# Lost Dog Tracer

Einrichtung und erste Schritte

## Einleitung

Lost Dog Tracer ist eine Web App zur Unterstützung bei der Suche nach entlaufenen Hunden. Der Hauptzweck besteht darin, verschiedenste Standort Informationen zu Sichtungen, Flyer Aktionen, Futterstellen, Fallen etc. an einer zentralen Stelle zu sammeln und bereitzustellen.

Insbesondere bei Flyer Aktionen kommen schnell dutzende Standorte zusammen. Hier ist es besonders wichtig ein einfaches zu bedienendes, schnelles Werkzeug zu Erfassung dieser Standorte zu haben. Dies war die Grundidee von Lost Dog Tracer. Mittlerweile wurde die App weiter ausgebaut und bei Bedarf auch weiter entwickelt.

Lost Dog Tracer steht als Open Source unter der MIT / Expat Lizenz zur freien Verfügung.

# Inhalt

Einleitung 1

1. Ersteinrichtung 3

1.1 Einrichtung „Web App“ auf Apple iOS (optional) 4

1.2 Einrichtung „Web App“ auf Android (optional) 6

1.3 Anmeldung und Profil 7

2. Menü / App Navigation 8

3. Standorte erfassen (vor Ort) 9

3.1 Offline Funktion 11

3.2 Einträge Bearbeiten 13

3.3 Kartenansicht 14

4. Fehlersuche 15

4.1 Zugriff auf Standortdaten durch die App (Browser) 15

4.1.1 Standort iOS 15

4.1.1 Standort Android 16

4.2 Updates und Reset 17

# 1. Ersteinrichtung

Lost Dog Tracer ist eine Web App, welche für die Nutzung mit Smartphones optimiert wurde. Sie benötigt keine Installation aus den App Stores der jeweiligen Anbieter. Ein gängiger Browser ist ausreichend. Getestet wurde die App auf folgenden Browsern:

- Safari (iOS)
- Edge (iOS, Android, Windows)
- Chrome (Android)

Die App wird sehr wahrscheinlich auch auf anderen Browsern funktionieren, es wird jedoch die Nutzung der aufgeführten Browser empfohlen.

**Hinweis: Die App kann komplett im Browser ausgeführt werden. Es ist jedoch wesentlich einfacher, sie als „Web App“ auf dem Home Screen des Smartphone zu installieren.**

Die App ist unterfolgendem Link zu erreichen:

https://lostdogtracer.kiefeld.org/

**Hinweis: Für die Nutzung der App ist eine Anmeldung erforderlich. Die Anmeldedaten werden vom betreibenden Verein bereitgestellt.**

Für die Einrichtung auf dem Home Screen folgen nun die Anleitungen für iOS (Schritt 1.1) und Android (1.2). Ist dies nicht gewünscht bitte mit Schritt 1.3 fortfahren.

## 1.1 Einrichtung „Web App“ auf Apple iOS (optional)

Die App muss zwingend mit dem **Safari Browser** geöffnet werden, um sie als Web App auf dem Home Screen einzurichten.

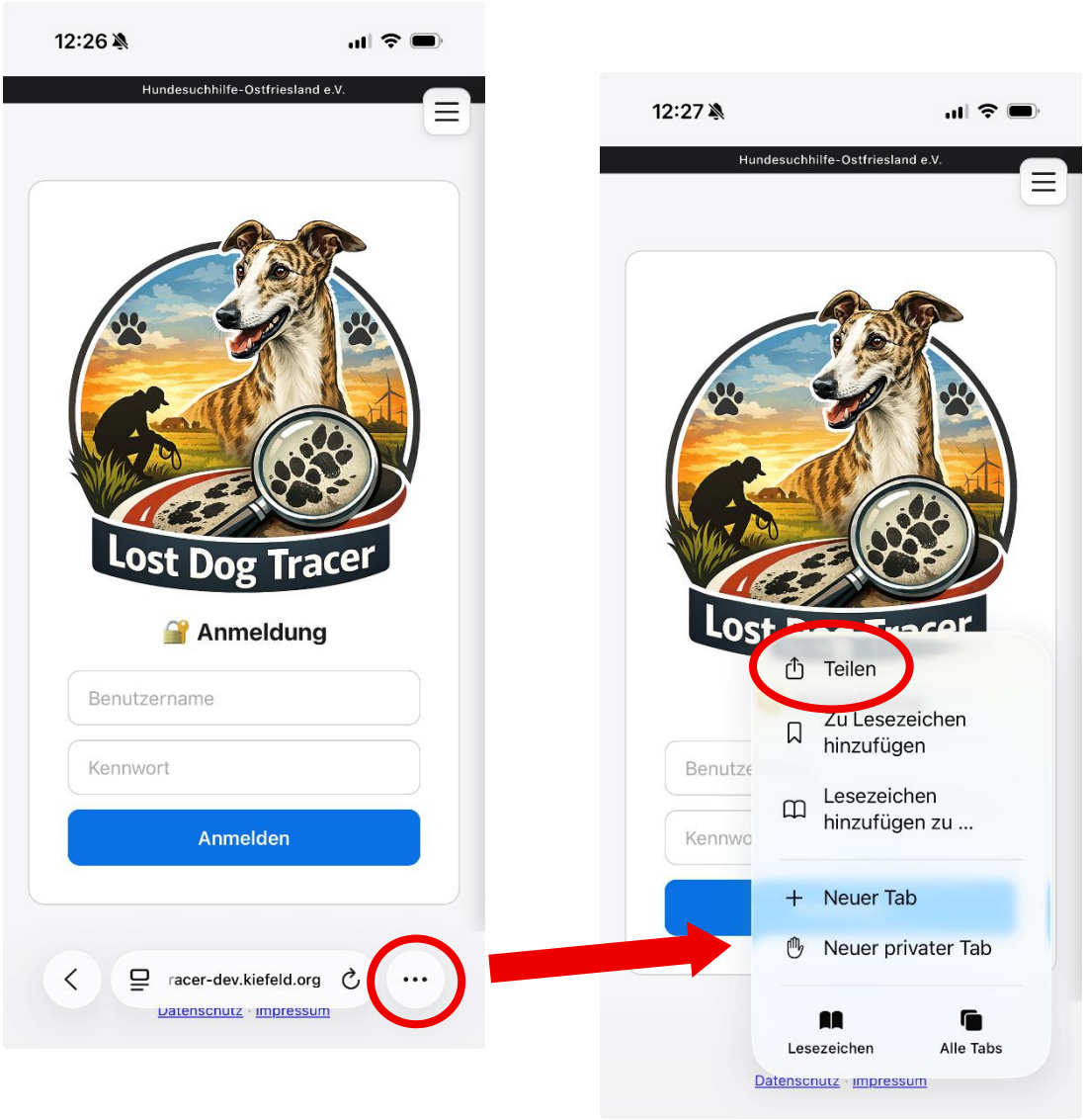


Wenn die App / Seite vollständig geladen wurde, öffne das ... Menü und wähle die Option „Teilen“.

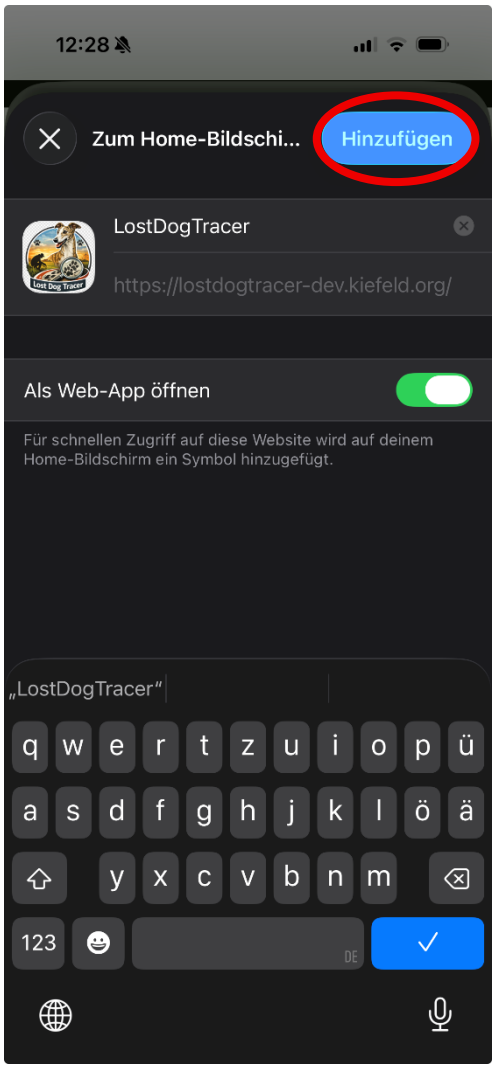


Eventuell musst du etwas hoch Scrollen, damit die Option "Zum Home-Bildschirm" erscheint. Bestätige die Aktion mit „Hinzufügen“. Du solltest die App nun auf deinem Home Screen finden:



## 1.2 Einrichtung „Web App“ auf Android (optional)

**Diese Anleitung ist KI generiert und eventuell nicht zu 100% korrekt.**

Die App sollte mit dem **Chrome Browser** geöffnet werden, um sie als Web App auf dem Home Screen einzurichten.

## 1.3 Anmeldung und Profil

Nach der ersten Anmeldung sollte umgehend das Passwort geändert werden.

**Hinweis: Das Passwort muss mindestens 8 Zeichen lang sein. Es gibt keine erzwungene Passwortkomplexität. Dennoch sollte kein zu einfaches Passwort verwendet werden, welches sich leicht erraten lässt.**

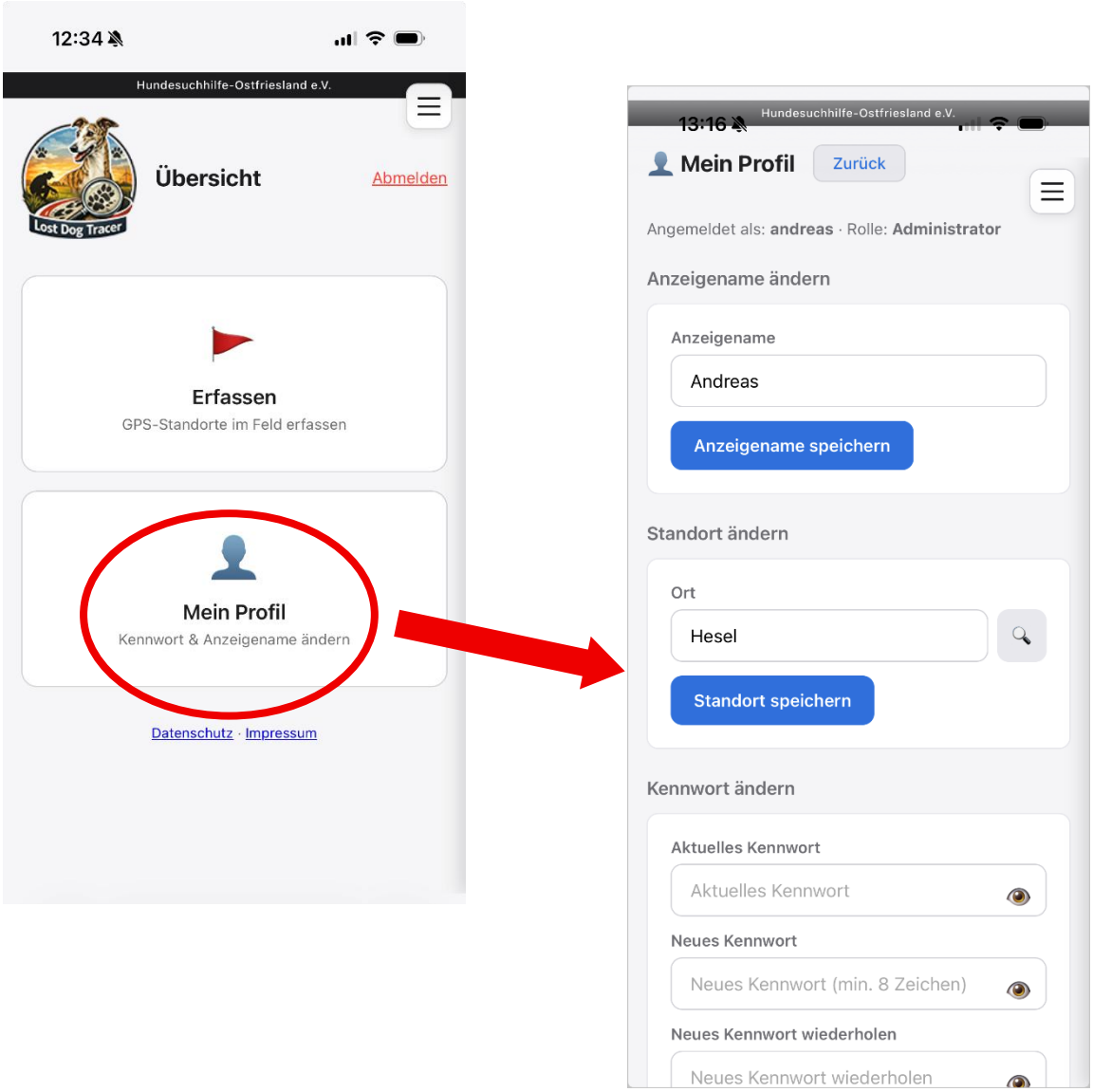


Der Anzeigename kann jederzeit geändert werden und hat keinen Einfluss auf die Verknüpfung zu den Standort Daten. Der Anmeldename kann nicht geändert werden und muss eindeutig sein!

**Wichtig! Das Profil speichert nur den Ort, nicht die komplette Adresse (Datenschutz). Daher muss z.B. für Aurich „Stadt Aurich“ eingegeben werden, sonst wird der Landkreis aufgelöst.**

# 2. Menü / App Navigation

Die Navigation ist denkbar einfach. Sie kann in Einzelschritten über Schaltflächen / Zurück Button erfolgen oder über das „Hamburger“ Menü oben rechts.

**Hinweis: Einzige Ausnahme, das „Erfassen“ hat aus verschiedenen Gründen (siehe weiter unten) keinen „zurück“ Button. Hier erfolgt die Navigation zurück nur über der Hamburger Menü.**

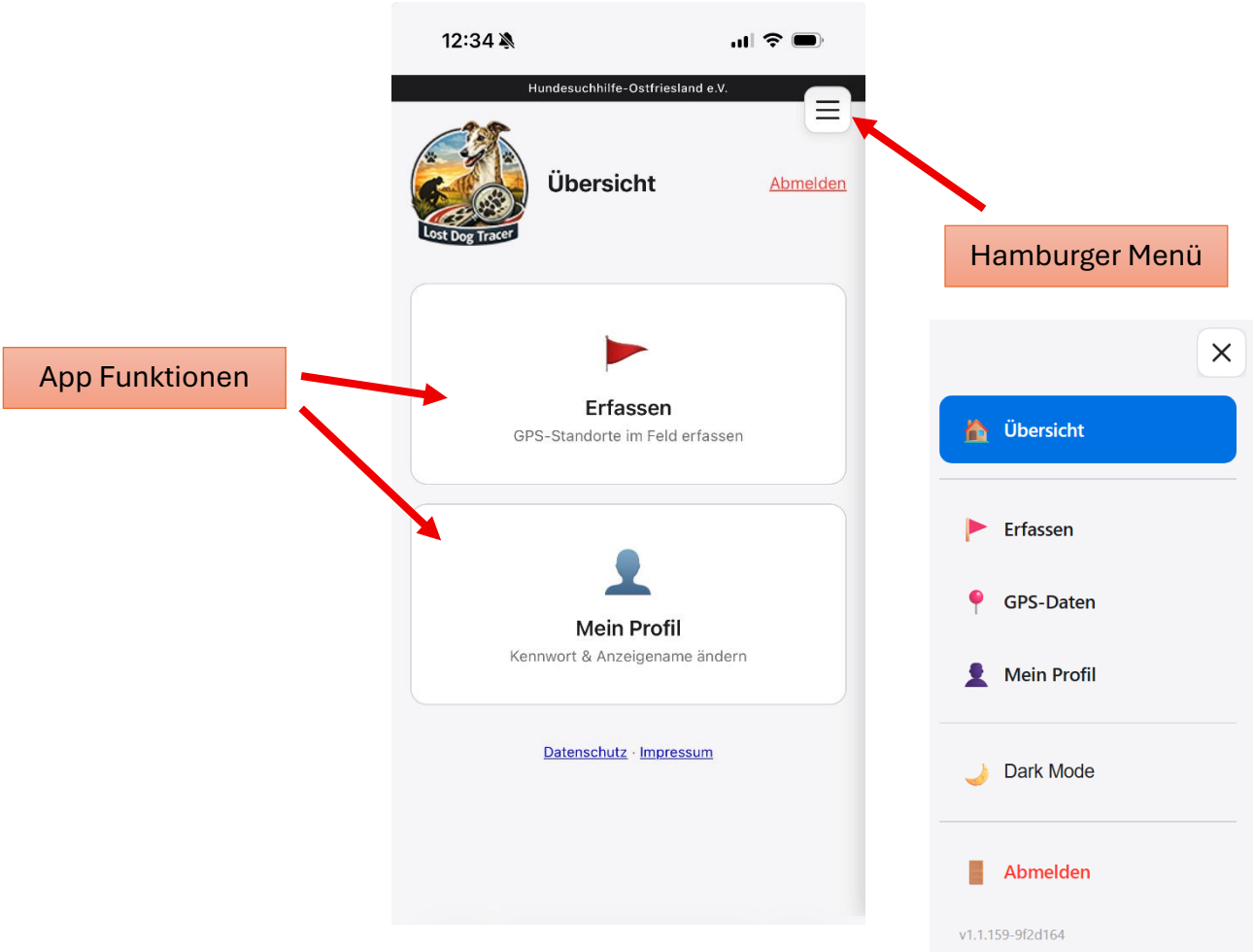

# 3. Standorte erfassen (vor Ort)

Die wichtigste Funktion der App ist die ursprüngliche Idee, währen der Flyer Aktion einfach und vor allem schnell den Standort des Flyer dokumentieren zu können.

Dein eigener Name wird automatisch übernommen. Der Name des Hundes sowie die Kategorie des zu speichernden Standortes muss ausgewählt werden. Erst dann wird der „Standort speichern“ Button blau und kann gedrückt werden.

**Hinweis: Die App speichert die zuletzt ausgewählten Daten. Daher müssen die Felder nicht jedes Mal neu ausgewählt werden.**

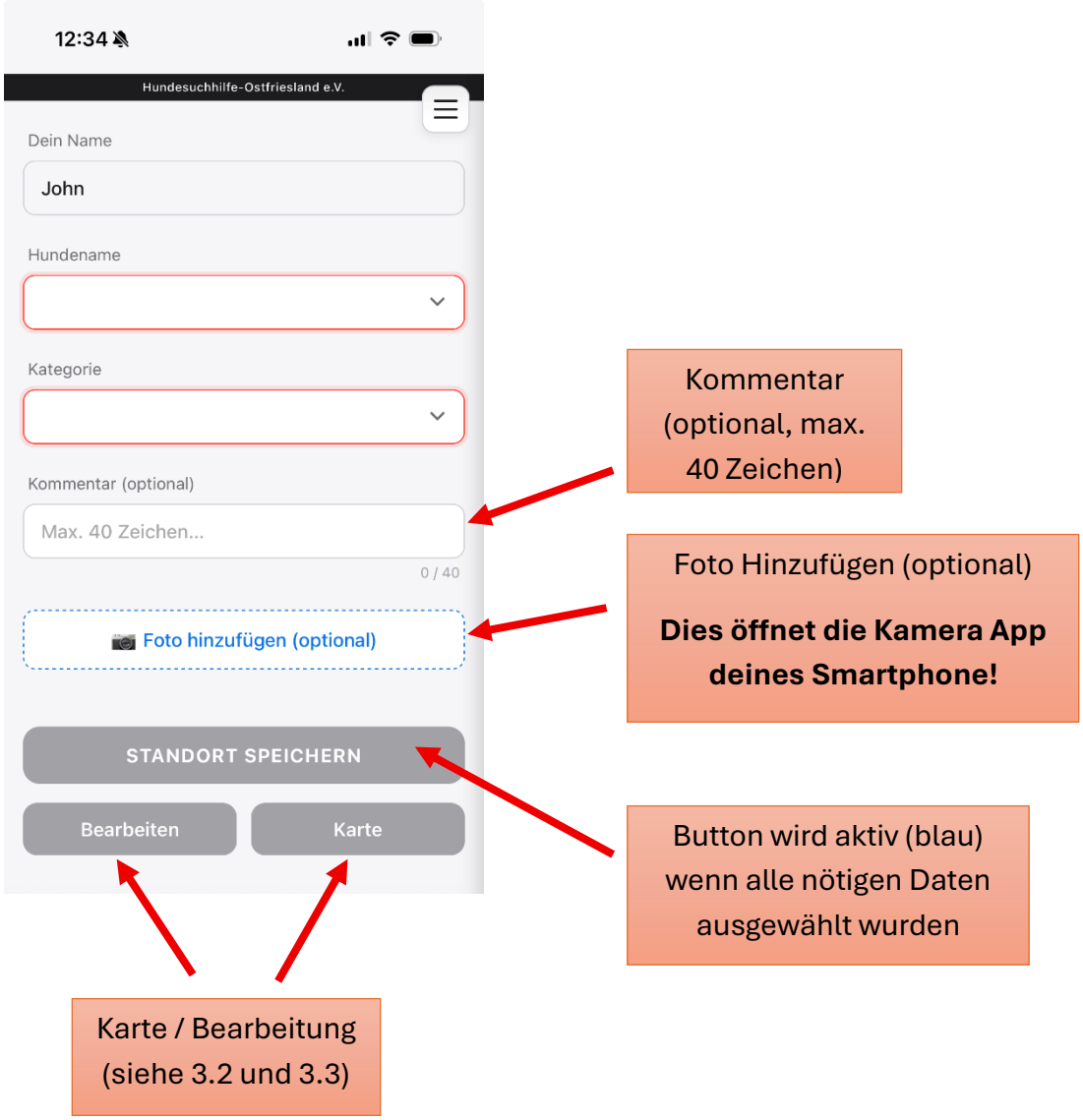

**Hinweis: Für die Funktion der App ist es zwingend erforderlich, dass der genutzte Browser Zugriff auf die Standort (GPS) Informationen des Smartphone hat (siehe auch unter "Fehlersuche"**

Wird der Standort speichern Button das Erste mal gedrückt, so muss der Anwender die Nutzung der Standortinformation bestätigen. Diese Aufforderung sollte danach nicht wieder erscheinen.

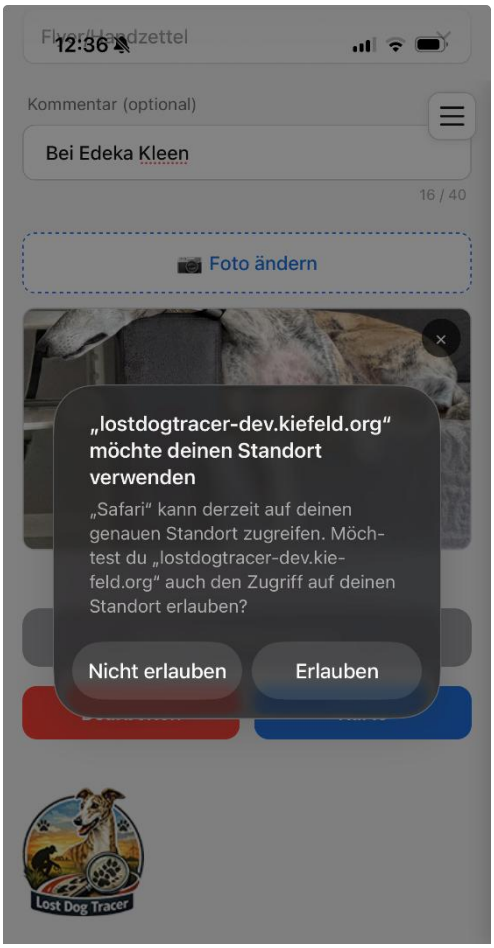

## 3.1 Offline Funktion

Die offline Funktion speichert automatisch neu erfasste Standorte auf dem Smartphone, bis wieder eine Verbindung zum Internet hergestellt werden kann. Diese Funktion soll die Nutzung der App auch in abgelegenen Regionen ohne ausreichende Mobilfunkabdeckung ermöglichen.

**Hinweis: Um die offline Funktion nutzen zu können müssen die App sowie die Funktion „Erfassen“ zuvor mindestens einmal geöffnet worden sein, so lange eine Internetverbindung besteht.**

**Wichtig: So lange Informationen offline gespeichert sind darf weder die App geschlossen werden noch darf die Funktion „Erfassen“ verlassen werden. Daher gibt es hier auch keinen „Zurück“ Button!**

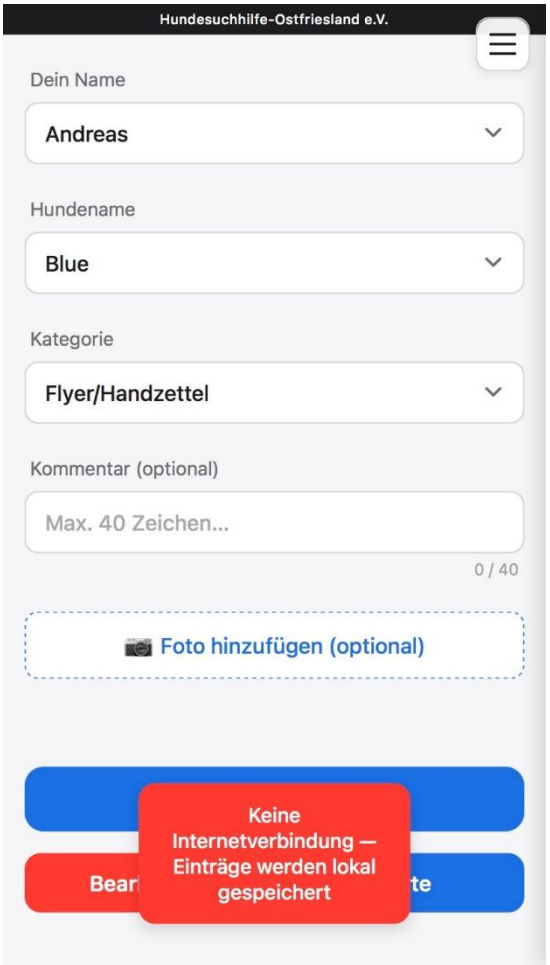

Werden Daten im offline Modus gespeichert so zeigt die App dies an. Ebenfalls wird angezeigt, sobald die Daten dann übertragen worden sind.

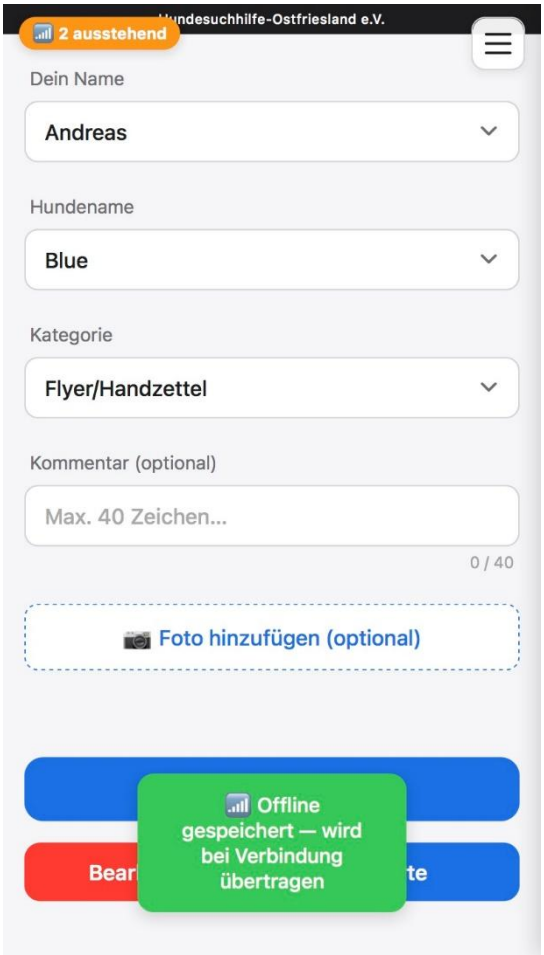

## 3.2 Einträge Bearbeiten

Diese Funktion dient primär dazu, falsch erfasste Standorte schnell und unkompliziert löschen zu können. Eine weitergehende Bearbeitung ist an anderer Stelle möglich.

**Hinweis: Das Löschen ist final und kann nicht rückgängig gemacht werden!**

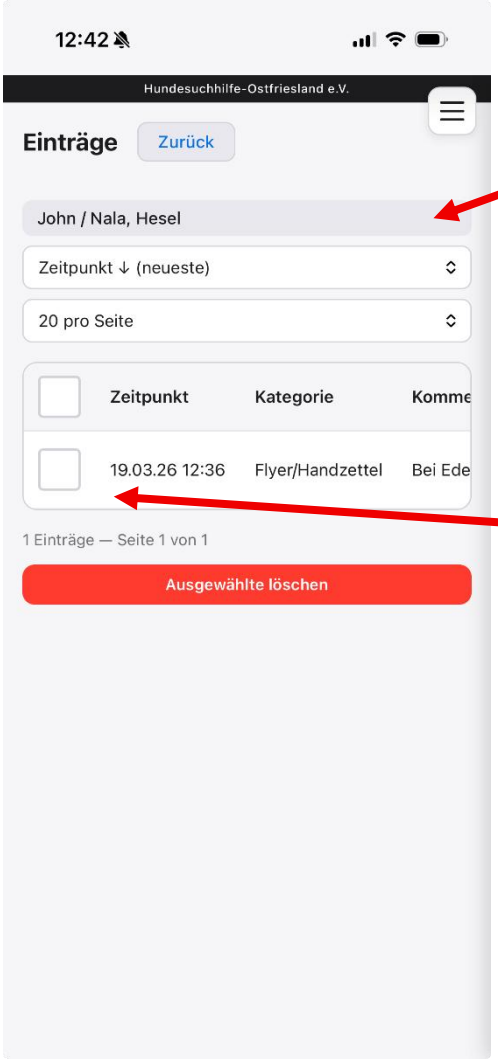


Die Kombination aus Namen und Hund ist auf Basis der Auswahl in der Erfassung vorselektiert

Es können einzelne oder mehrere Einträge selektiert und gelöscht werden.

## 3.3 Kartenansicht

Die Kartenansicht in der Erfassung dient ebenfalls nur zu schnelle und unkomplizierten Kontrolle der Einträge. Eine weitergehende Bearbeitung ist an anderer Stelle möglich.

**Hinweis: Das Löschen ist final und kann nicht rückgängig gemacht werden!**

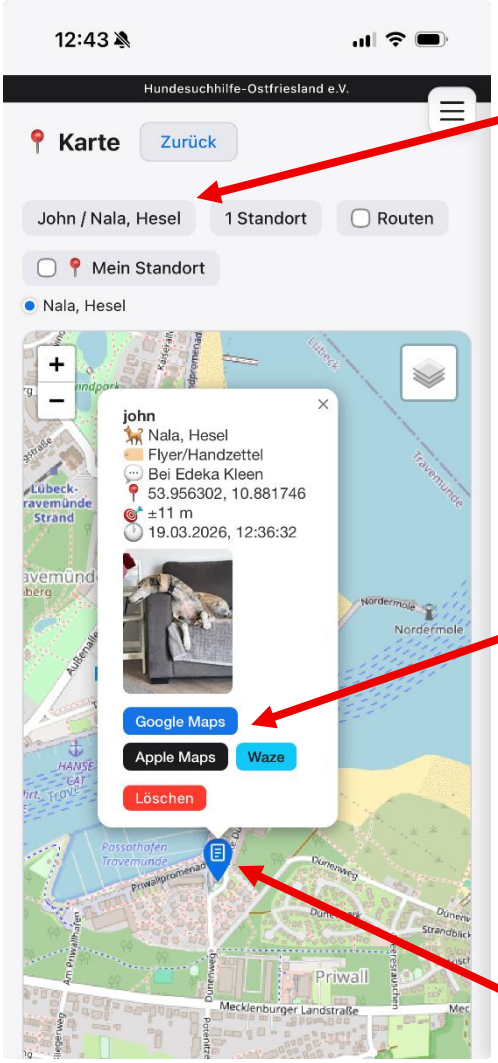


Die Kombination aus Namen und Hund ist auf Basis der Auswahl in der Erfassung vorselektiert

Um zum Standort zu navigieren kann die gewünschte App aufgerufen werden

Die Auswahl des Kartenmarker zeigt umfassende Informationen zum Standort

# 4. Fehlersuche

## 4.1 Zugriff auf Standortdaten durch die App (Browser)

Der Zugriff auf den Standort ist bei allen Smartphones im Standard eingeschränkt. In der Regel muss der Benutzer im Web Browser den Zugriff auf den Standort für jede Webseite bestätigen (siehe Abschnitt 3). Es ist jedoch auch möglich, den Zugriff auf den Standort für den Browser komplett zu sperren. In diesem Fall funktioniert die App nicht mehr.

### 4.1.1 Standort iOS

Bei iOS finden sich die Optionen unter **Einstellungen -> Apps -> [App Name] (Safari)**

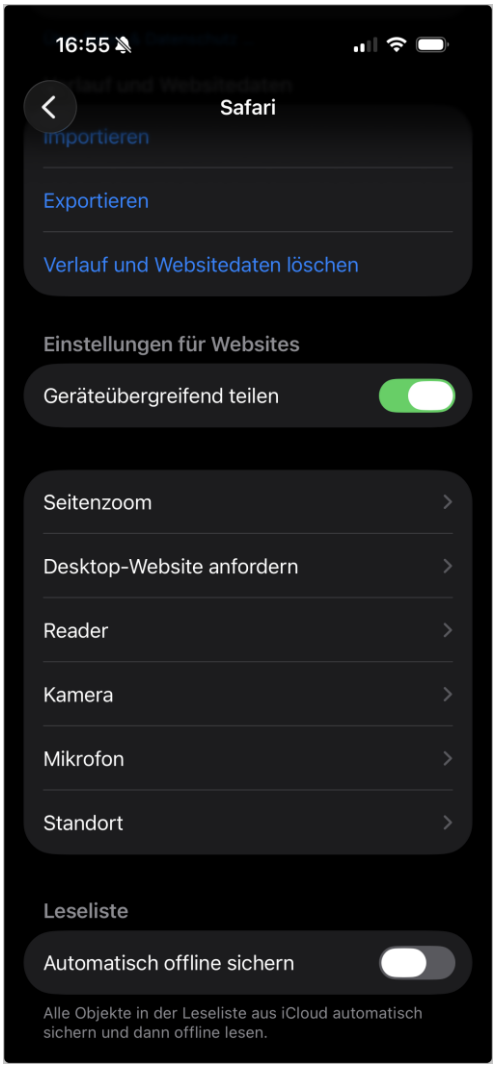


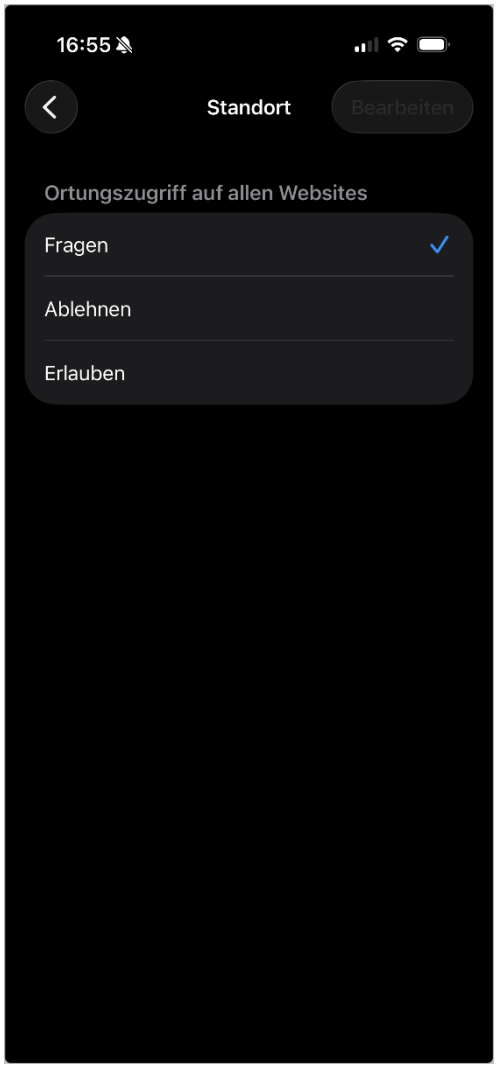


Die Einstellung sollte „Fragen“ sein (Standard, empfohlen) oder „Erlauben“ (nicht empfohlen)

## 4.1.1 Standort Android

**Diese Anleitung ist KI generiert und eventuell nicht zu 100% korrekt.**

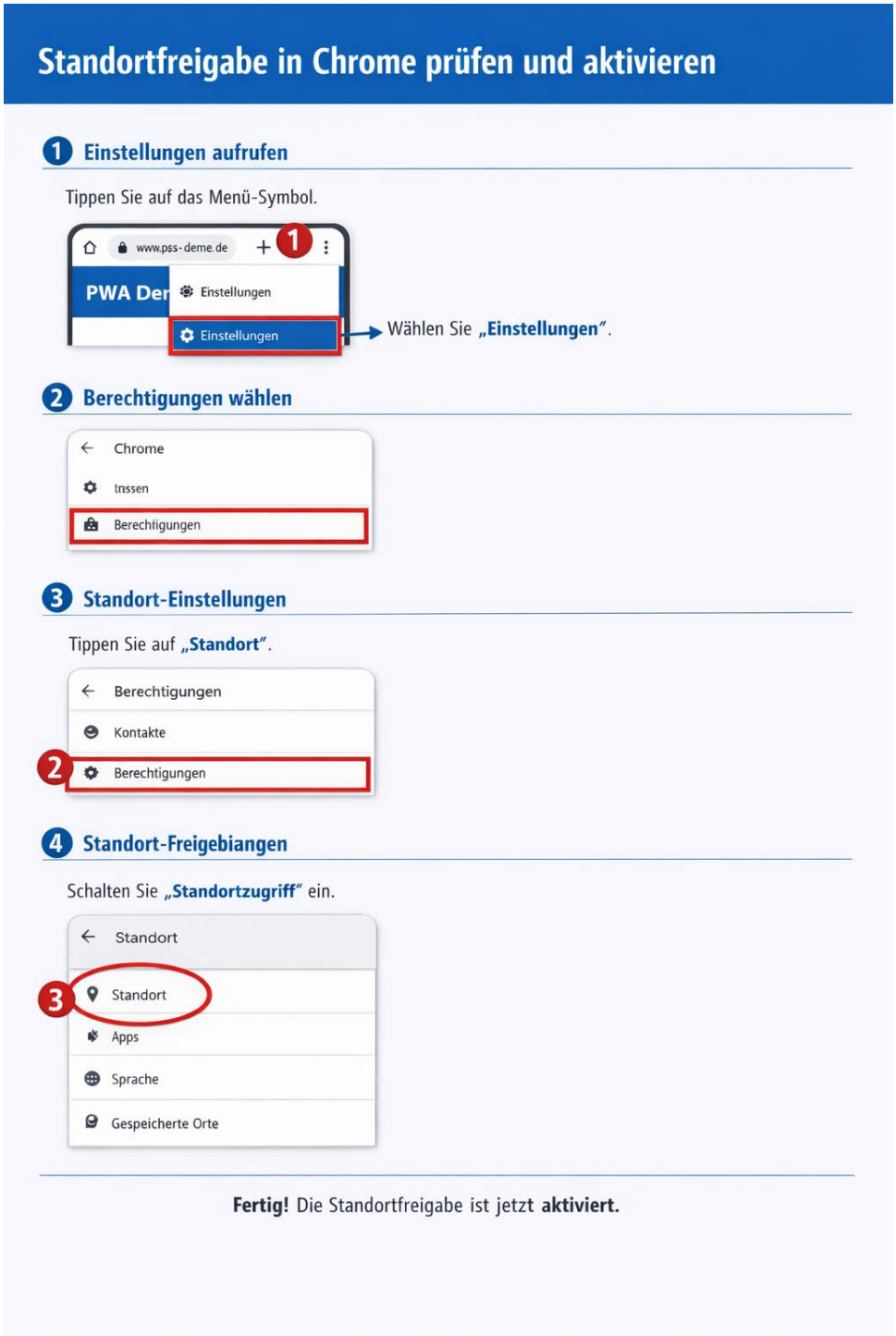

## 4.2 Updates und Reset

Die App wird bei Bedarf aktualisiert. Auf Grund der Architektur wird ein großer Teil der Daten lokal zwischengespeichert. Dies sorgt für ein schnelles Laden sowie die offline Fähigkeit. Allerdings kann es in seltenen Fällen passieren, dass ein Update nicht sofort auf dem Endgerät angezeigt wird. In diesem Fall kann ein kompletter Reset der App durchgeführt werden.

**Hinweis: Bei diesem Reset werden keine gespeicherten Daten gelöscht!**

**Wichtig: Der Reset darf nicht ausgeführt werden, so lange sich noch offline Daten auf dem Endgerät befinden!**

Der Reset Button befindet sich im Hamburger Menü. Hier kann auch die Version geprüft werden: